LYS LEZ LANNOY

et ses alentours

DANS LA DÉBÂCLE DE 1940

Mai 1940. Le sol de l' agglomération lilloise, habituellement paisible, tremble sous le fracas de la guerre. À Lys-lez-Lannoy et dans les environs, l'heure est à la panique alors que la débâcle s'abat sur l'armée franco-britannique. Au cœur de cette tourmente, des structures de béton, les blockhaus, se dressent comme des sentinelles silencieuses, témoins de résistances désespérées. Ce livre vous plonge au cœur de ces événements dramatiques, explorant le contexte qui a mené à cette bataille perdue et l'héritage laissé par cette période sombre de notre histoire.

Abréviations utilisées :

Blockhaus : Structure de défense en béton armé, conçue pour résister aux tirs d'artillerie et abriter des troupes ou des armes.

Ligne Maginot : Système de fortifications construit par la France le long de ses frontières orientales et alpines après la Première Guerre mondiale, dans le but de se protéger contre une éventuelle attaque allemande.

Ligne Daladier : Ligne de fortifications construite en urgence à la frontière franco-belge après la proclamation de neutralité de la Belgique en 1937.

DCA (Défense Contre Avions) : Ensemble des moyens et des tactiques utilisés pour se défendre contre les attaques aériennes.

Télémètre : Instrument optique utilisé pour mesurer la distance d'un objet, ici pour régler le tir des canons anti-aériens.

Drôle de guerre : Période de la Seconde Guerre mondiale (de septembre 1939 à mai 1940) caractérisée par une absence de combats majeurs sur le front occidental. Le terme vient de l'anglais "phoney war" (fausse guerre). Corps expéditionnaire britannique (BEF) : Force militaire envoyée par le Royaume-Uni pour soutenir la France au début de la Seconde Guerre mondiale.

Secteur Défensif de Lille (SDL) / Secteur Fortifié de Lille (SFL) : Zone fortifiée le long de la frontière franco-belge, faisant partie de la ligne Maginot.

Pillbox : Terme britannique désignant un petit blockhaus.

Royals Engineers : Corps du génie de l'armée britannique, responsable de la construction et de la maintenance des fortifications.

FM (Fusil-Mitrailleur) : Arme automatique portative, plus légère qu'une mitrailleuse, utilisée pour le soutien d'infanterie.

Fossés antichars : Tranchées creusées pour gêner la progression des blindés.

Tranchées : Fossés creusés dans le sol pour offrir une protection aux soldats contre les tirs ennemis.

Oreillon : Pièce bétonnée ajoutée à un créneau pour protéger contre les tirs venant des côtés.

Créneau : Ouverture dans une fortification permettant de tirer tout en étant protégé.

Secteur Fortifié des Flandres / Secteur Fortifié de l'Escaut : Autres secteurs fortifiés faisant partie de la ligne Maginot.

"Gort Line" : Nom donné par les Britanniques à la ligne de défense le long de la frontière franco-belge.

Panzers : Terme allemand désignant les chars de combat.

B.E.F : British Expeditionary Force.

1. Contexte général

Après la Grande Guerre, la France et le Royaume-Uni ont deux visions différentes, la France sent le besoin de se protéger initialement de l'Italie fasciste de Mussolini puis de l'Allemagne nazie tandis que le Royaume-Uni vise une méthode d'apaisement.

Les Britanniques ne veulent plus revivre la douleur de la grande guerre. Pendant des années le Royaume-Uni laisse l'Allemagne faire pour éviter une nouvelle guerre destructrice comme par exemple lors de l'annexion des Sudètes par l'Allemagne en octobre 1938.

Pendant ce temps, la France construit depuis 1928 la Ligne Maginot, une succession de fortifications censée protéger la frontière Est et la frontière Alpine. En 1937, la belgique proclame sa neutralité, il est décidé en urgence de construire une ligne de fortification à la frontière franco-belge.

Le projet est en partie soutenu par le ministre Édouard Daladier, cette ligne sera nommée "Ligne Daladier".

2. L’entre deux guerres

Entre les deux guerres (1914-1918 et 1939-1945), la France essaye de se reconstruire aussi bien dans le domaine civil que militaire. Dans les environs, un réarmement de la frontière se fait voir. Au début des années 1930, plusieurs positions de DCA sont mises en place pour assurer la défense du secteur. Les positions ne sont pas occupées, en attente d’une éventuelle attaque. À Wattrelos, dans la plaine de Beaulieu, une batterie constituée de 4 cuves bétonnées pour canons de 75 mm Anti-Aérien est mise en place. Plus loin, un télémètre devait évaluer la distance des avions afin de régler le tir des canons. Une des 4 cuves est encore visible dans un champ.

La cuve restante.

Comme expliqué précédemment, en 1937 il est décidé de construire des blockhaus le long de la frontière belge. Lys Lez Lannoy n’y échappera pas car 2 blockhaus seront construits par les français en 1937 (nous en parlerons dans un chapitre dédié).

3. La mobilisation des troupes

En septembre 1939, l'équilibre fragile de l'Europe bascule brutalement. Le 1er septembre, l'Allemagne attaque la Pologne sans déclaration de guerre, forçant la France et le Royaume Uni à sortir de la diplomatie et à entrer officiellement dans le conflit. Très vite, la mobilisation s'accélère : les ordres de rappel sont lancés, les unités se mettent en mouvement, les gares se remplissent de soldats, et l'armée française se déploie dans l'attente d'un choc que beaucoup croient imminent. Une première action est menée dans la Sarre, davantage comme une reconnaissance offensive et un test des dispositifs adverses que comme une véritable opération destinée à percer. Mais le 17 septembre, l'invasion de la Pologne par l'URSS achève de convaincre l'état-major français que le sort de ce pays est désormais scellé. Les troupes engagées se replient alors vers leurs positions défensives, principalement sur la ligne Maginot. Et, contre toute attente, le front se fige : les semaines passent sans affrontements d'ampleur, dans une attente tendue et incertaine qui prend bientôt un nom resté célèbre, la « drôle de guerre ». À l'automne, cette mobilisation prend une dimension nouvelle avec l'arrivée en France du corps expéditionnaire britannique (British Expeditionary Force), venu épauler le dispositif allié et s'installer progressivement sur la frontière franco-belge, tandis que populations et soldats s'habituent à une guerre déclarée… mais encore lointaine, suspendue entre préparation fébrile et silence inquiétant.

Les unitées

À Lys Lez Lannoy, c'est le 100ème régiment d'infanterie qui prend en charge la zone. Le 13 Novembre, après l'arrivée des troupes britanniques, les unités françaises sont prépositionnées. La 6ème compagnie du 2ème bataillon du 201ème R.I se positionne à Lys Lez Lannoy et le P.C est établi à Cohem tandis que la 7ème compagnie se positionne sur Leers. Le 30 Novembre 1939, les troupes françaises sont repositionnées dans la Meuse et la BEF (corps expéditionnaire britannique) prend le contrôle de la zone Armentières-Lecelles. C'est le 2ème bataillon des Coldstream Guards qui se positionne à Lys Lez Lannoy et les Grenadiers Guards à Hem. Les Britanniques réquisitionnent le château Masure (maintenant parc maréchal) probablement pour installer un poste de commandement.

A Wattrelos, les soldats du 406ème RAA (régiment antiaérien) se positionnent dans les cuves pour canons de Beaulieu.

La BEF (British Expeditionary Force)

La BEF étaient divisée en 3 corps :

I Corps

Lieutenant-General Barker
- 48th Motor Infantry Division
- 1st Infantry Division
- 2nd Infantry Division

II Corps

Lieutenant-General Brooke
- 50th Motor Infantry Division
- 3rd Infantry Division
- 4th Infantry Division

III Corps (à partir d'avril 1940)

Lieutenant-General Adam
- 5th Infantry Division
- 44th Infantry Division
- 42th Infantry Division

La BEF à été déployée autour de Lille (d'Armentières à Lecelles) afin d'aider les français dans la manœuvre Dyle-Breda qui consistait à envoyer les troupes sur le sol Belge pour enliser le front comme pendant la grande guerre.

Le Plan Dyle

Le plan Dyle est un plan d'action adopté par la France et le Royaume-Uni en 1939. Il vise à faire face à une éventuelle attaque allemande à l'Ouest. Les chefs militaires français pensent alors que l'armée allemande passera principalement par la Belgique, comme lors de la Première Guerre mondiale. Le principe du plan Dyle consiste à faire avancer rapidement les armées françaises et britanniques en Belgique, afin d'établir une ligne de défense le long de la rivière Dyle, entre Anvers et Namur. Cette stratégie a pour objectif de protéger la Belgique, de défendre la France loin de ses frontières et d'éviter les destructions sur le territoire français.

4. Les blockhaus

Lys Lez Lannoy fait partie de la ligne Daladier, plus précisément le Secteur Défensif de Lille (SDL renommé Secteur Fortifié de Lille (SFL) en Mars 1940). En 1937 deux blockhaus furent construits par les français. C'est le 16ème Régiment régional de travailleurs qui les construira.

Le blockhaus "Bloc de Lys Les Lannoy" lors de sa construction en 1937.
Source : Wikimedia Commons, B294 - Lys-lez-Lannoy.jpg
Nous pouvons observer que le blockhaus était équipé d'une mitrailleuse Hotchkiss modèle 1914 car son trépied est visible au premier plan de l'image.

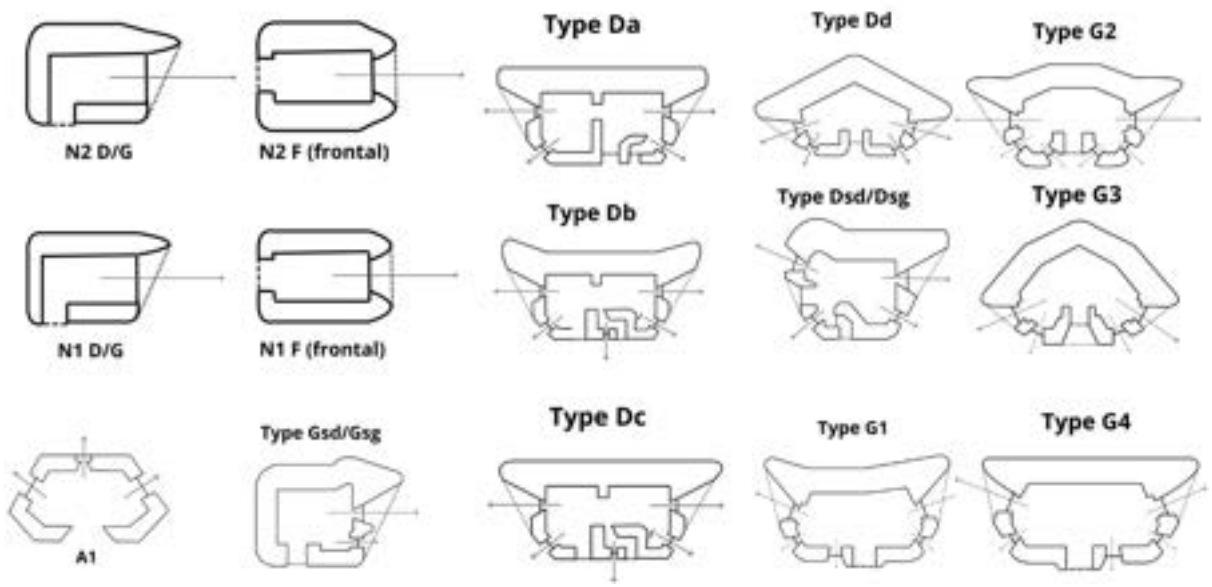

Plans des blockhaus du Secteur Fortifié de Lille.

Sur Lys, ce sont des blockhaus types G1 (Bloc de Lys Lez Lannoy) et Dd (Bloc du Fresnoy).

Un blockhaus type G1 encore visible au parc du héron à Forest-sur-Marque.

Un type Dd.

Les blockhaus français étaient équipés de portes blindées, voici les différent types de portes :



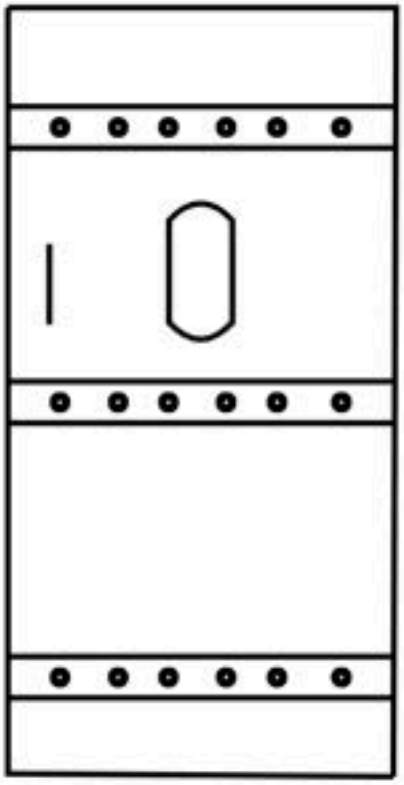

Une porte de type A avec un créneau de tir pour FM 24/29.



Porte de type B.

Porte de type C avec un créneau de tir pour fm 24/29.



Porte de type D.

Les blockhaus français avaient leur date inscrite au-dessus de leur porte à l'aide d'un cartouche. Cette date correspondait à la date de commencement des travaux.

Le cartouche de construction d'un blockhaus. Celui-ci indique 1938 comme date de commencement des travaux.

En novembre 1939, l’état major britannique n’est pas convaincu des défenses réalisées par les français et décide de renforcer les défenses. 8 Blockhaus supplémentaires sont construits par les “Royals Engineers”. Ces nouveaux blockhaus sont appelés “Pillbox” par les Anglais en référence de leurs formes ressemblant à des boîtes à pilules.

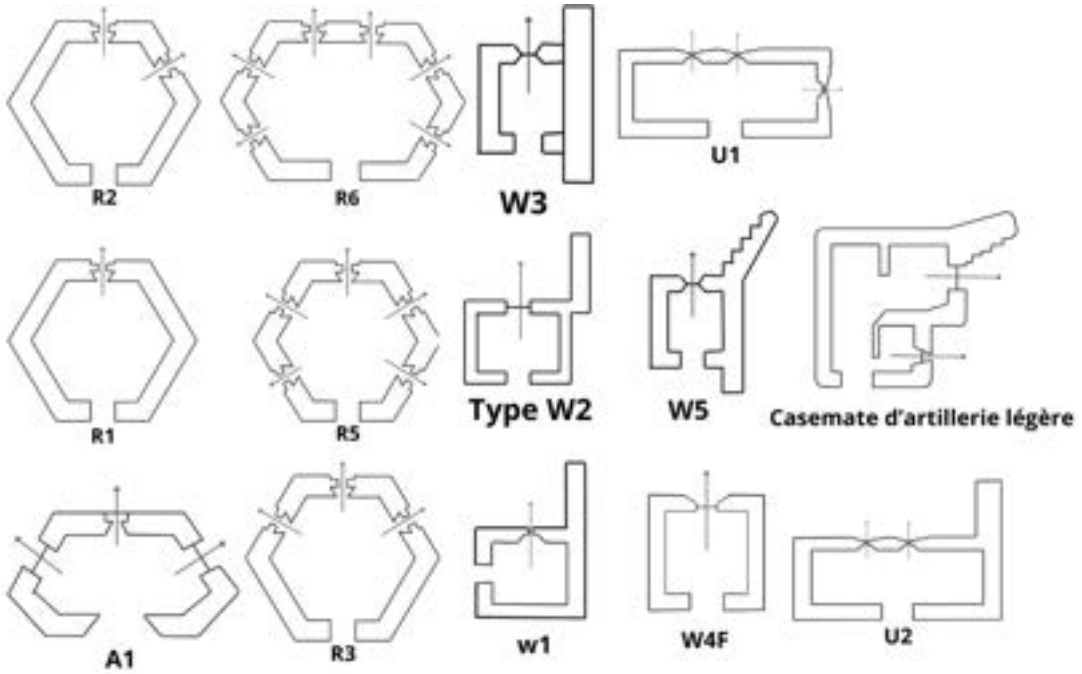

Plans des types de Pillboxes.

Dénomination	Type de blockhaus	Constructeur
Bloc du Fresnoy	Dd	Français (16ème RRT)
Bloc de Lys Lez Lannoy	G1	Français (16ème RRT)
Pillbox du Vert Près	U2	BEF (Royal Engineers)
Pillbox de Cohem Nord	W5g	BEF (Royal Engineers)
Pillbox de Cohem Centre	R5	BEF (Royal Engineers)
Pillbox de Cohem Sud	R	BEF (Royal Engineers)
Pillbox de Lys Lez Lannoy	R	BEF (Royal Engineers)
Pillbox du Bon Poste Ouest	R	BEF (Royal Engineers)

Pillbox du Bon Poste Est	W4	BEF (Royal Engineers)
Pillbox de la Chapelle Madame	W5g	BEF (Royal Engineers)

Liste des blockhaus construits à Lys Lez Lannoy.

Les Pillboxes types R et U2 sont conçus pour avoir comme armement des fusils mitrailleurs Bren et les Pillboxes types W4 et W5 sont conçus pour recevoir un canon.

Le Pillbox de Lys Lez Lannoy dans son état actuel.

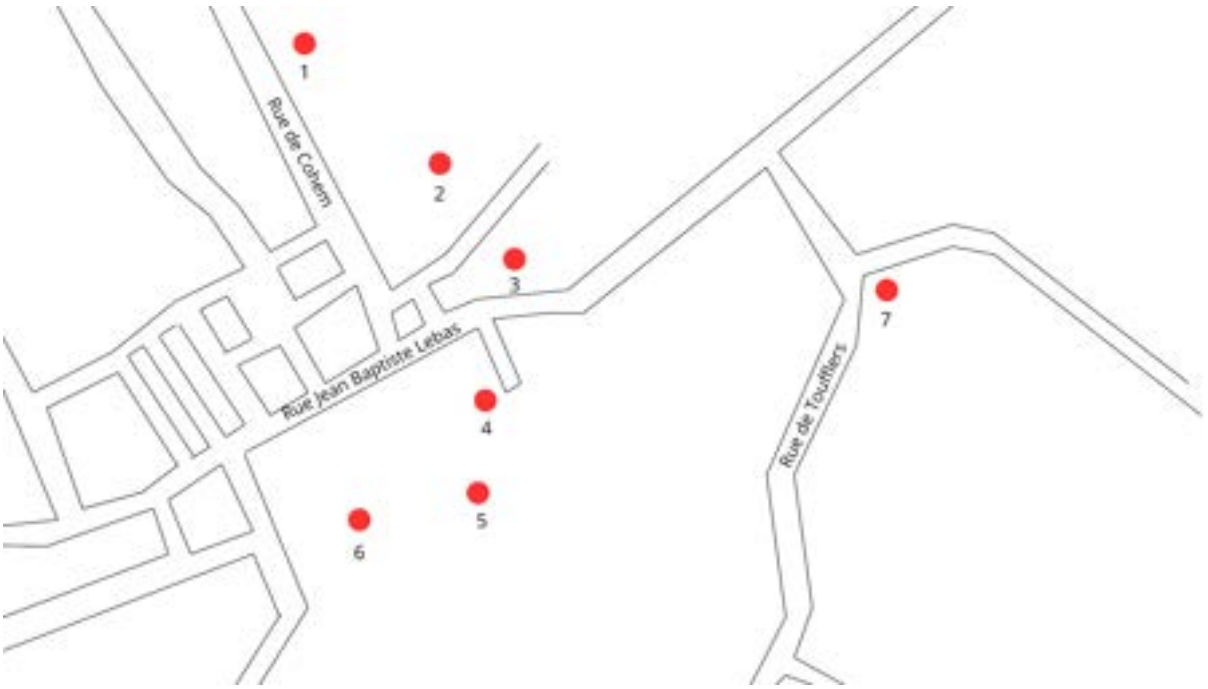

Plan du secteur de cohem en 1940.

Nom	Numéro
Pillbox du Vert Près	1
Pillbox de Cohem Nord	2
Pillbox de cohem Centre	3
Pillbox de Cohem Sud	4
Bloc de Lys Lez Lannoy	5
Pillbox de Lys Lez Lannoy	6
Bloc du Fresnoy	7

Le Bloc de Lys Lez Lannoy

Le bloc de lys lez lannoy a été construit en 1937, il s'agit d'un bloc type G1 et était armé de deux mitrailleuses hotchkiss modèle 1914 (si on regarde au premier plan de la photo de 1937). Le bloc était équipé de deux créneaux principaux (normalement prévu pour des canons) et de 3 (+1 sur la porte) créneaux pour Fusils Mitrailleurs pour la défense rapprochée. Il était équipé d'une porte type C, d'un périscope pour observer les alentours et était équipé d'une ventilation forcée à bras. Des volets en fer étaient posés devant les créneaux principaux pour les protéger quand les canons n'étaient pas installés. Le bloc à été démoli en 2005 pour construire le quartier du béguinage.

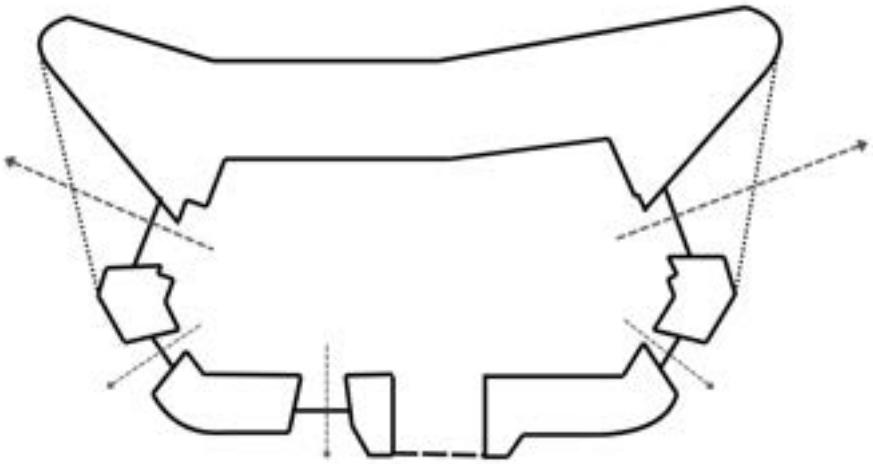

Schéma du bloc

Le Bloc du Fresnoy

Le bloc du Fresnoy a été construit en 1937, il s'agit d'un bloc type Dd. Le bloc était équipé de deux créneaux principaux (normalement prévu pour des canons) et de 2 (+1 sur la porte) créneaux pour Fusils Mitrailleurs pour la défense rapprochée. Il était équipé d'une porte type C, d'un périscope pour observer les alentours et était équipé d'une ventilation forcée à bras. Des volets en fer étaient posés devant les créneaux principaux pour les protéger quand les canons n'étaient pas installés.

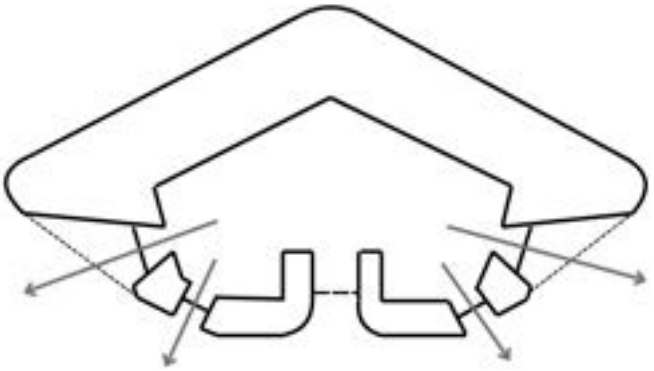

Schéma du bloc

Le bloc dans un jardin privé

Le pillbox du Vert Près

Le pillbox du Vert Près a été construit en 1939, il s'agit d'un pillbox type U2g (pillbox de flanquement flanquant à gauche) . Le pillbox était équipé de deux créneaux pour fusils mitrailleurs BREN ou mitrailleuses. Il tirait sur une zone non couverte par les tirs des blockhaus Français et complétait le tir du pillbox de Cohem Nord. Le pillbox est en état de ruine dans un jardin privé.

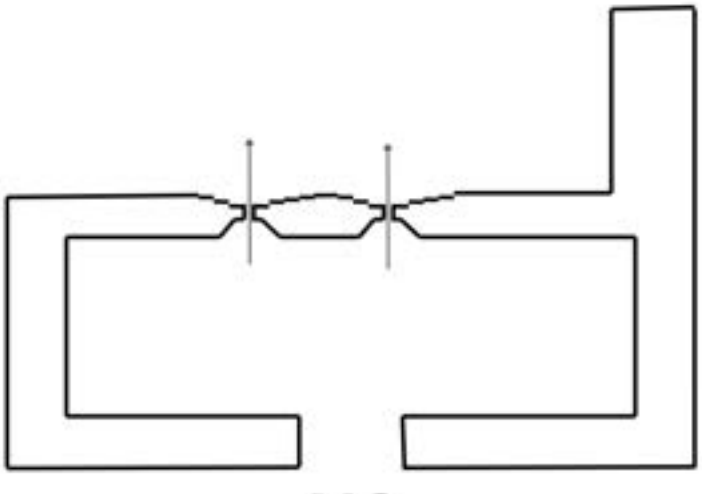

Schéma d'un pillbox type U2g.

Le pillbox de cohem Nord

Le pillbox de Cohem Nord a été construit en 1939, il s'agit d'un pillbox type W5g (pillbox de flanquement flanquant à gauche) . Le pillbox était équipé d'un seul créneau pour un canon. Il était équipé d'un périscope pour observer les alentours. Sous le créneau, il y a une attache pour accrocher un canon de 25mm afin de limiter le recul. Il tirait sur une zone non couverte par les tirs des blockhaus Français (Nord).

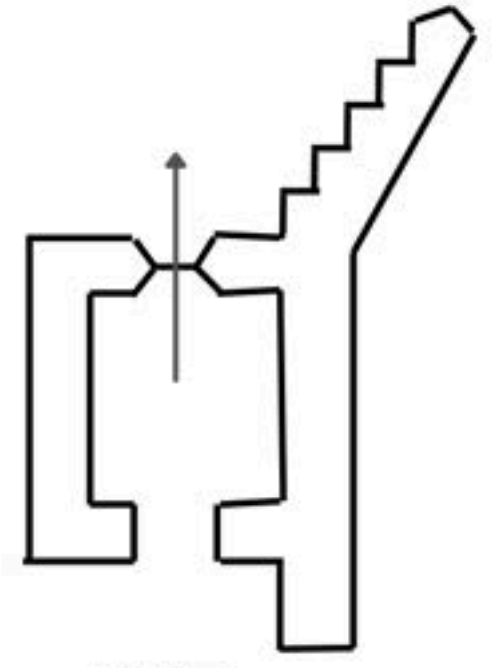

Schéma du pillbox

Le pillbox.

L’orifice pour le périscope.

L’attache canon.

Pillboxes de Cohem Centre et Sud

Les pillboxes de Cohem Centre et Sud sont des pillboxes types R5 (Modèle hexagonal avec 5 créneaux). Ils étaient armés de fusils mitrailleurs BREN ou de mitrailleuses.

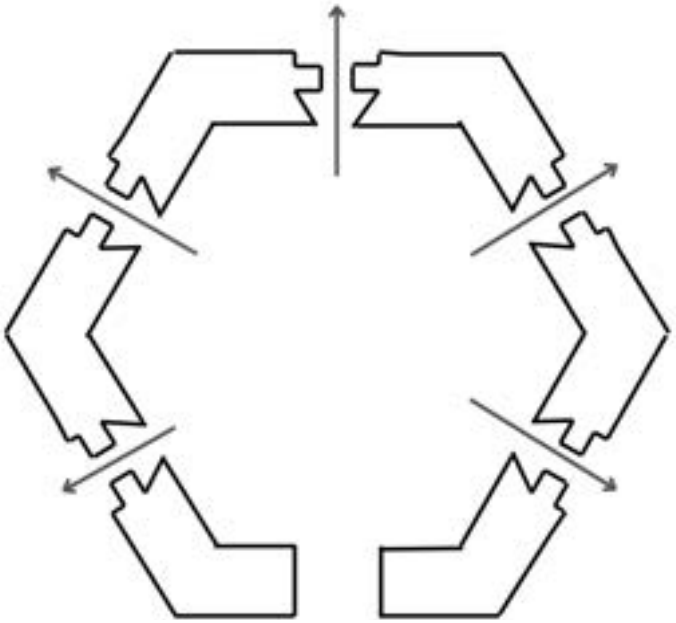

Schéma du pillbox type R5

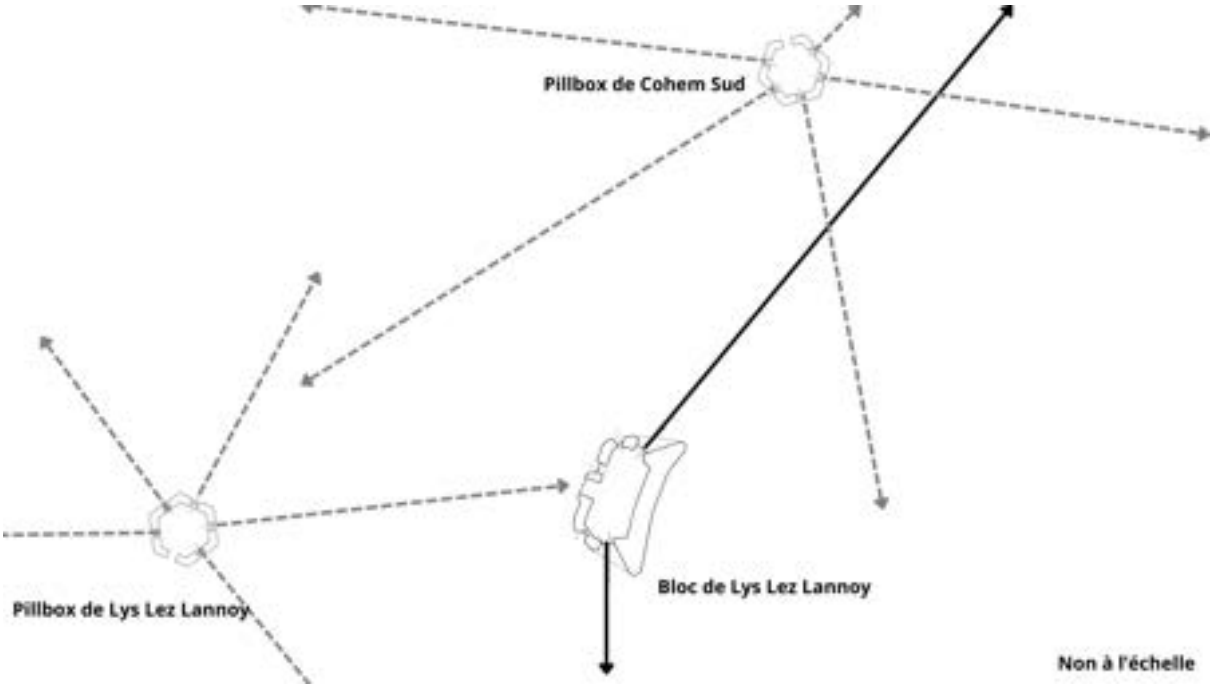

Plan de feu du Pillbox de Cohem Sud, Pillbox de Lys Lez Lannoy et Bloc de Lys Lez Lannoy (non à l'échelle).

Le pillbox de Lys Lez Lannoy

Ce pillbox est un pillbox type R dont le type exact reste inconnu. Sa fonction était de protéger la tranchée derrière le bloc de Lys Lez Lannoy. Il était équipé d'un ou des fusils mitrailleurs BREN.

Le pillbox.

Les autres pillboxes

Plus au sud, au bon poste, il y avait un pillbox type R et un autre de type W4 (les deux ont disparu pour construire une école). A la chapelle madame, il y a aussi un blockhaus de type W5g complétant le tir du bloc de Toufflers Sud.

Coûts de constructions des blockhaus

Les blockhaus ont un certain coût de construction, pour le bloc du Fresnoy c'est 295.000 F (soit environ 204.000€ en 2026) et 420 m³ de béton et pour le bloc de Lys Lez Lannoy c'est environ 300.000 F qui ont étaient dépensés.

Type de Pillbox	Coût en béton (en Tonnes)
R	127
U2	250
W5	152

Coût unitaire en béton des types de Pillboxes construits par la BEF à Lys Lez Lannoy.

La construction des pillboxes

La construction d'un pill box est en plusieur parties :

les fouilles

pose du premier ferraillage



coulage du radier

coulage en plusieurs parties des murs

Pour réaliser les murs, les soldats utilisent des planches de coffrage posées à l'horizontale.

coulage de la dalle de toit (vue de dessus)



Pour couler la dalle de toit, les soldats s’aident d’une rampe en bois pour faire monter les chariots et les outils.

pause de crépit (ou camouflage)

Des soldats construisent un pill box (photo : imperial war museum)

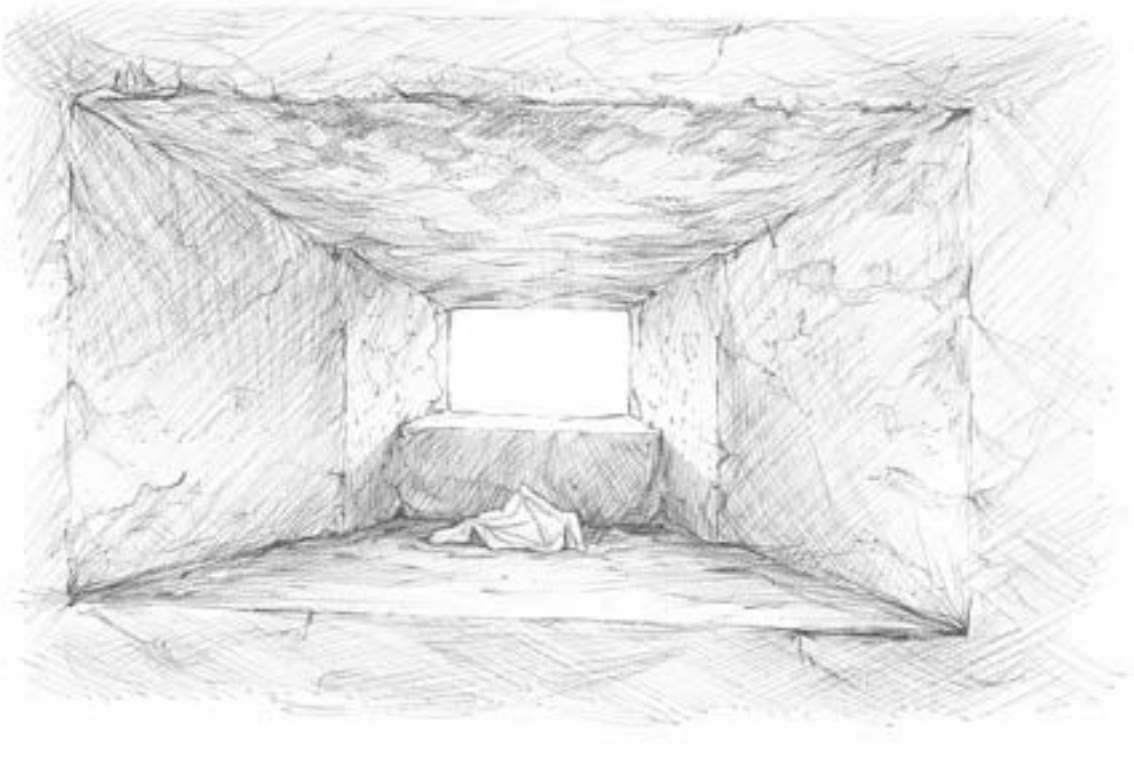

Schéma d’un créneau d’un Pillbox.

Le camouflage

Le camouflage des blockhaus français était bicolore.

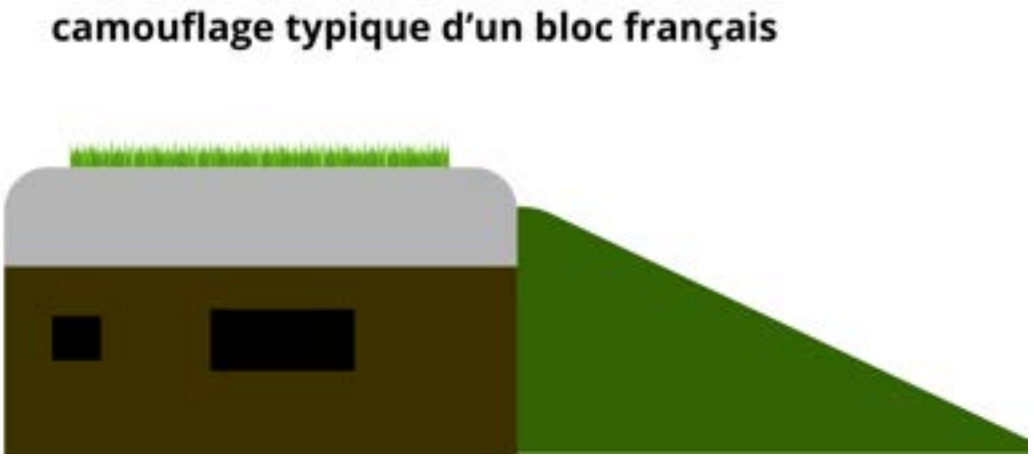

Les cartouches de constructions étaient aussi peints.

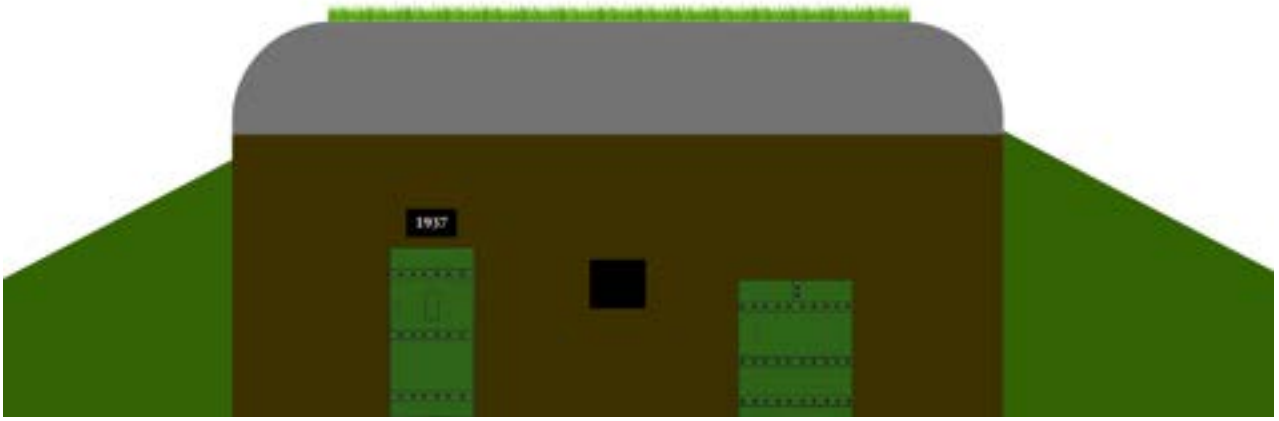

Camouflage d'un bloc français vu de sa porte

Pour les pillboxes construits par la BEF, il était souvent camouflés dans des corps de fermes, avec des briques, avec une bute de terre,...

Un blockhaus d'observation camouflé en façade à Mouchin (photo : imperial war museum)

Les autres types de constructions défensives

Bien que la plupart des ses constructions sont des blockhaus, d'autres constructions furent construites.

Les tourelles STG (Section Technique du Génie)

Ces tourelles démontables étaient armées de mitrailleuses Hotchkiss et étaient assemblées par 8 hommes. Elles étaient placées dans des encuvements prévus à cet effet. Elles étaient le plus souvent placées à côté des voies de chemin de fer ou à côté des ponts.L'équipage était de 2 hommes, un tireur et un chargeur. L'entrée se faisaient par l'arrière grâce à une petite porte

Encuvement bétonné pour une tourelle démontable à Wattrelos.

Tourelle STG à la casemate du mont des Bruyères.

Les réseaux de rails antichars

Les réseaux de rails antichars étaient disposés en 3 rangées. Ils devaient servir à stopper, ou du moins, ralentir les chars pour les forcer à rouler sur les routes pour maximiser l'efficacité des blockhaus. Ils étaient aussi ajoutés à un réseau de fils barbelés. Des rails usés étaient aussi utilisés pour économiser les ressources.

Réseau de rails antichars à l'ouvrage de la ferté.

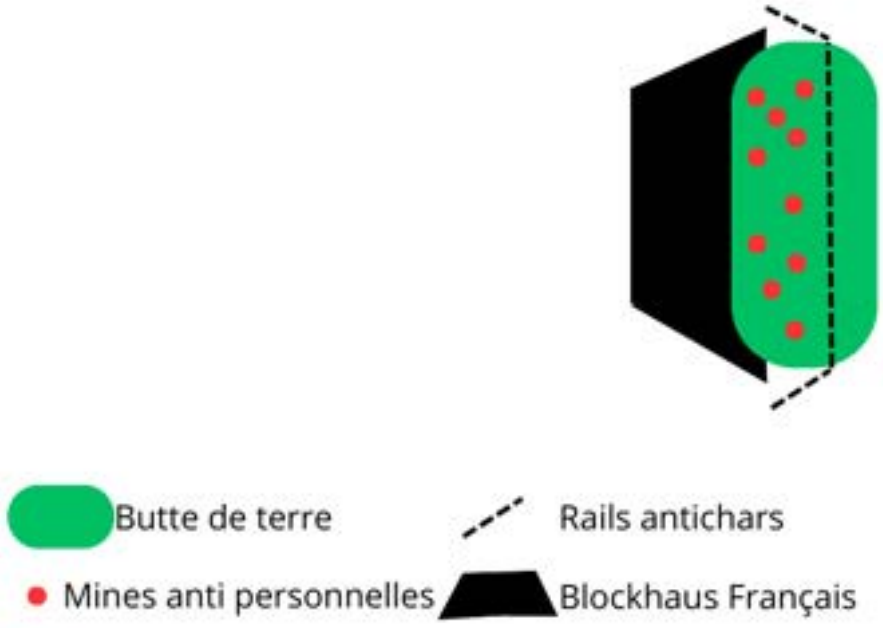

Schéma de l’organisation d’un réseau de rails antichars.

Les barrages cointet

Les barrages cointet ou “porte belge” étaient des barrages mis en place sur les routes pour empêcher les véhicules de passer.

ici, des soldats Britanniques et Français devant un barrage cointet (photo : Imperial War Museum)

À Lys Lez Lannoy, un barrage de ce type a été mis en place rue de Toufflers. Il devait empêcher les véhicules venant de belgique de passer, il était complété par le feu du bloc du Fresnoy.

Schéma du barrage du Fresnoy.

Les fossés antichars ont étaient aussi utilisés entre chaque blockhaus pour ajouter un protection supplémentaire contre les blindés.



Schéma d'un fossé antichars Français.

Un réseau antipersonnel et antichar à Halluin. (Nous pouvons apercevoir au troisième plan à droite ce qui semble être le bloc du triez cailloux.) (photo : Imperial War Museum).

Les tranchées

Comme pendant la grande guerre, les soldats creusent des tranchées entre les blockhaus soit pour relier les blockhaus, soit pour offrir une protection contre l'infanterie ennemie. Les tranchées pour relier les blockhaus entre eux sont en forme de Z et celles pour la défense sont de formes rectangulaires (voir les schémas).

Schéma d'une tranchée d'accès à un blockhaus.

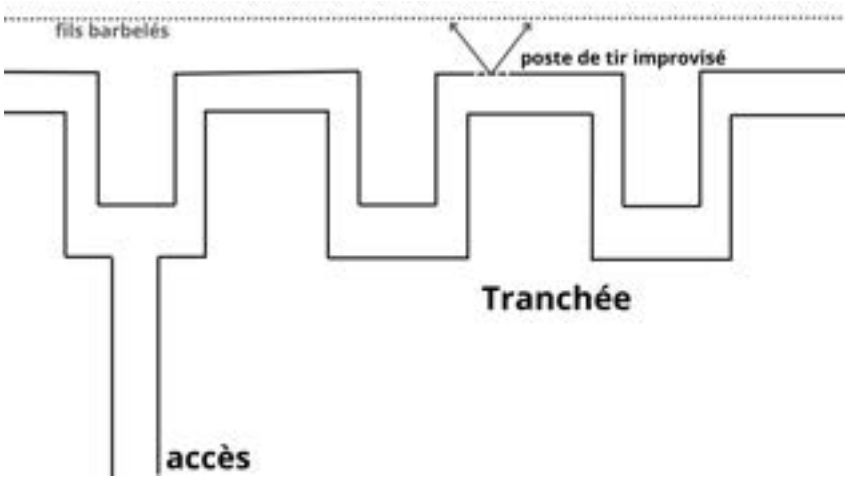

Schéma d'une tranchée défensive.

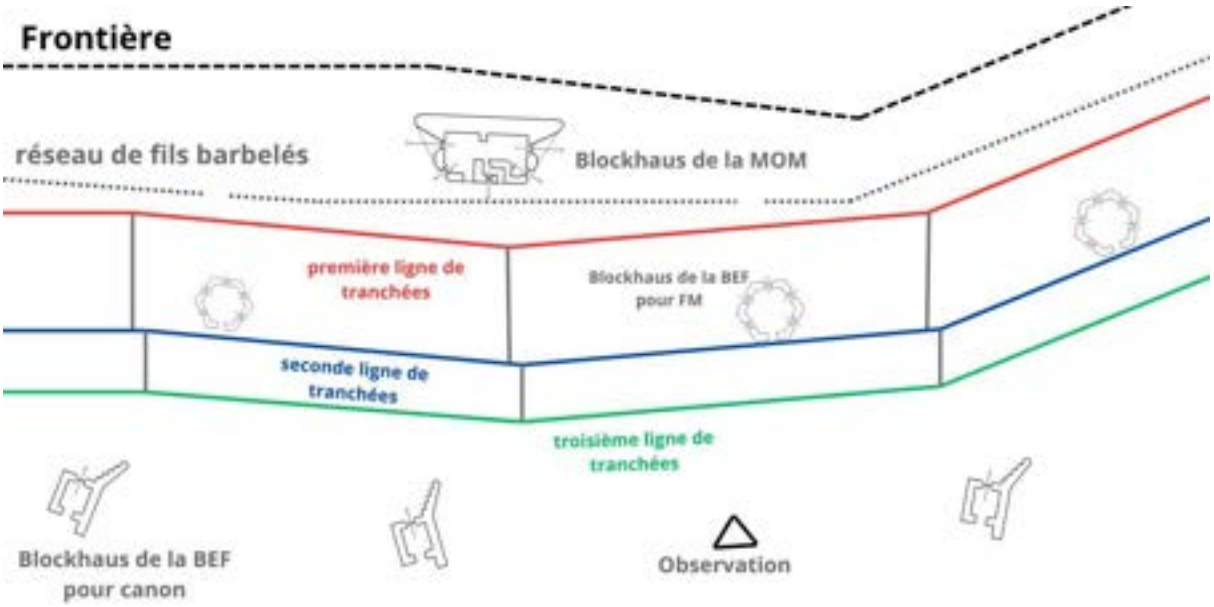

Schéma de la tactique utilisée pour les tranchées (celle-ci peut changer en fonction du terrain).

La tactique utilisée

Dès le début de la construction du SFL, l'état-major Français décida d'appliquer une tactique dite de “flanquement” car le terrain autour de Lille n'avait pas de barrière naturelle (ex:montagnes). Cette tactique consiste à ne pas tirer en face de l'ennemi mais de tirer sur les côtés. Cette tactique sert à agrandir le champ d’action du blockhaus et permet de s’entraider entres blockhaus.

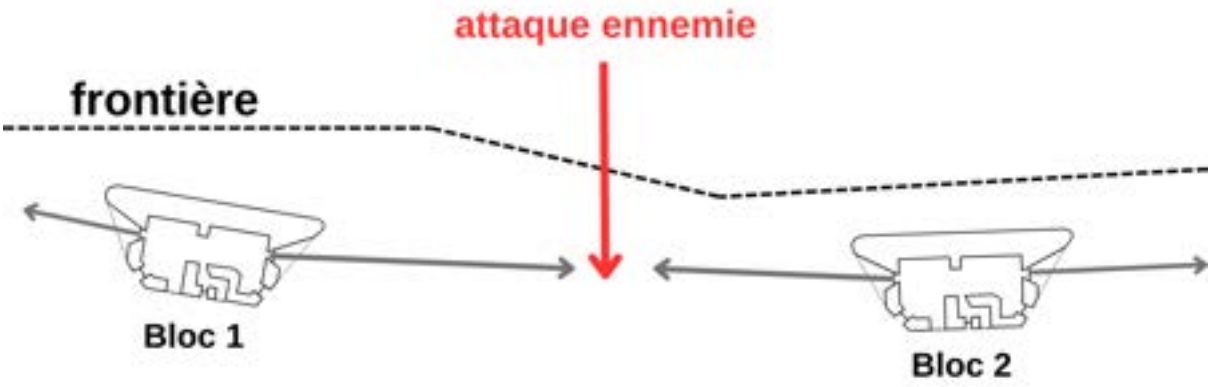

Schéma de la tactique de flanquement.

Il existe tout de même des blockhaus avec une tactique dite “frontale”. Celle-ci consiste à tirer en face de son objectif. Cette tactique était appliquée pour protéger des ponts, voies ferrées ou d’autres points stratégiques. Cette tactique a été très peu utilisée du fait que la Belgique était neutre.

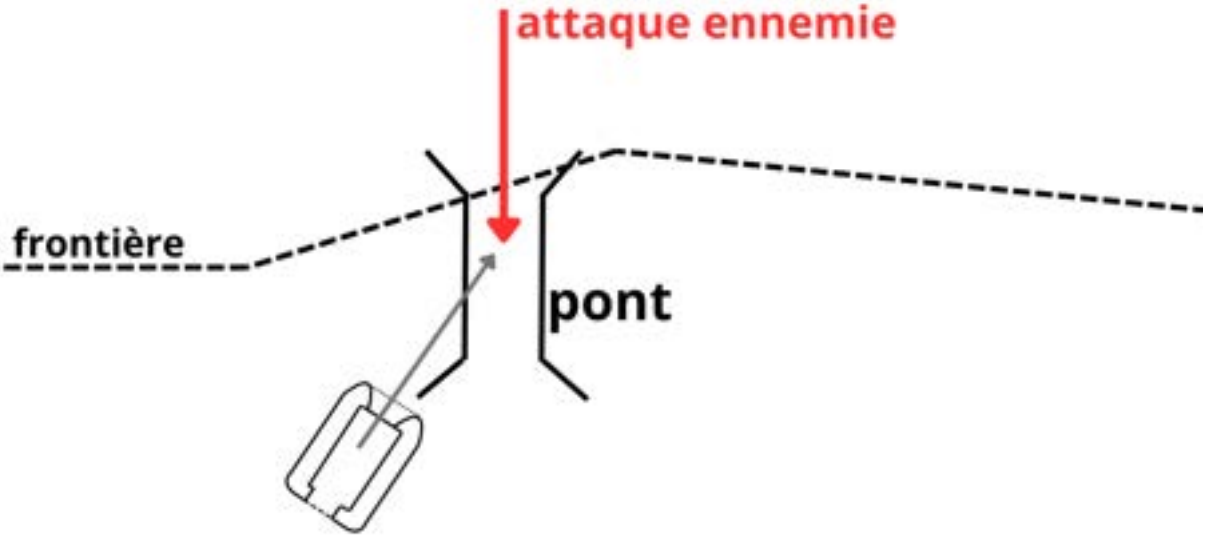

Schéma de la tactique du frontal.

La tactique anglaise

Les anglais ont compris pendant la première guerre mondiale qu'une arme automatique pouvait infliger de gros dégâts. Dès l'arrivée de la BEF en octobre 1939, les anglais ont opté pour une tactique de frontal. Les blockhaus anglais de flanquements ont été souvent utilisés pour une tactique frontale. Les blockhaus anglais de flanquements se démarquent des autres avec l'ajout d'un oreillon protégeant le créneau des tirs venant de droite ou gauche.

Oreillon d'un blockhaus anglais de flanquement.

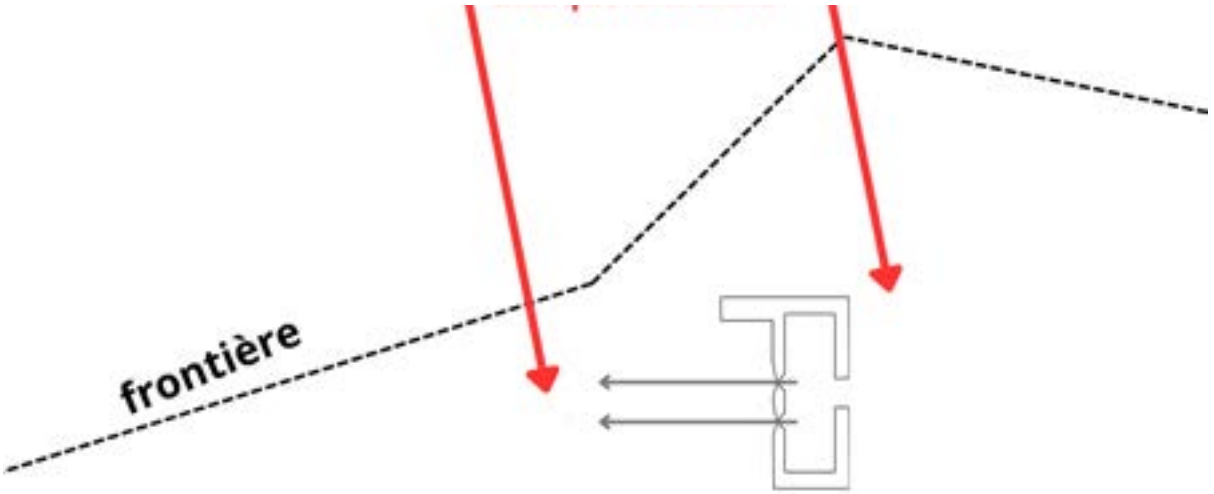

Schéma de la tactique anglaise de flanquement.

Même si la moitié des blockhaus anglais sont des blockhaus de flanquement, l'autre moitié étaient des blockhaus frontaux. Contrairement aux blockhaus français, les blockhaus anglais n'étaient pas placés spécialement au points stratégiques mais directement à la frontière.

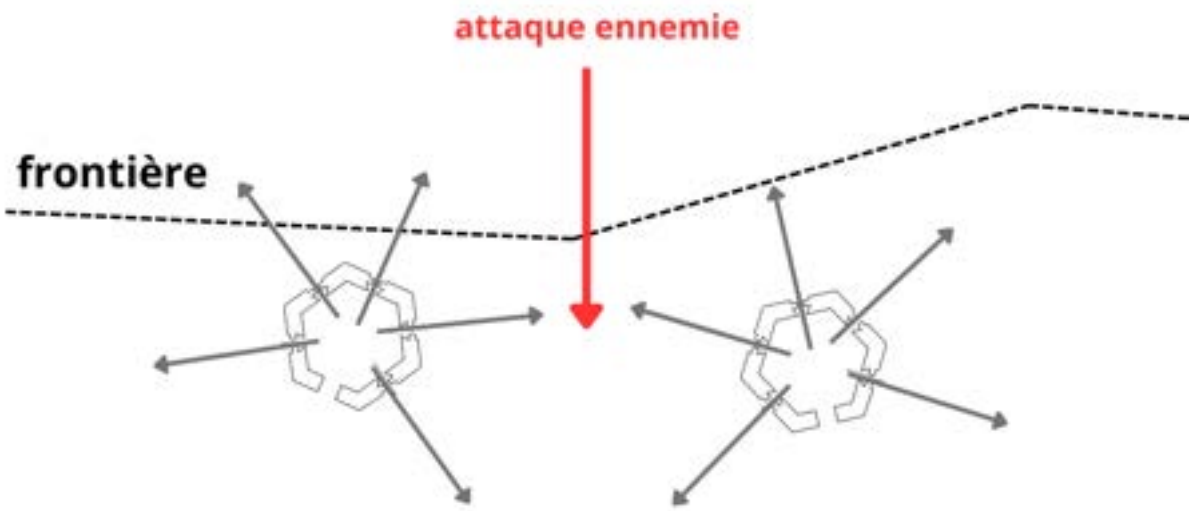

Schéma de la tactique anglaise du frontal.

5. L’armement de la Ligne

Les Canons

-le canon de 25mm hotchkiss SA 34

Le canon de 25mm hotchkiss SA 34 était un canon antichar Français semi-automatique conçu en 1934. Il avait une cadence de tir de 20 coups/minute et tirait des obus de 25mm.

Un canon Hotchkiss de 25mm SA34 utilisé par le BEF
(photo : imperial war museum)

utilisation dans les blockhaus : France de 1937 à 1939, BEF de 1939 à 1940.

Douille de 25 mm.

-le canon de 2 pdr

Le canon de 2 pdr (pounder) était un canon antichar Anglais. Il avait une cadence de tir de 22 coups/minute et tirait des obus de 40mm.

Un canon de 2 pdr (photo : imperial war museum)

Les mitrailleuses

-la mitrailleuse hotchkiss de 8mm

La mitrailleuse hotchkiss de 8mm était une mitrailleuse Française conçue en 1914. Elle avait une cadence de tir de 400 coups/minute et tirait des cartouches de 8mm lebel dans une bande chargeur rigide contenant 24 cartouches.

Une mitrailleuse Hotchkiss à la casemate du mont des bruyères ©les blockhaus lyssois

utilisation dans les blockhaus : France de 1937 à 1939

-la mitrailleuse Vickers

La mitrailleuse Vickers était une mitrailleuse Britannique rentrée en service en 1912. Elle avait une cadence de tir de 500 coups/minute et tirait des cartouches de .303 british dans une bande chargeur souple contenant 250 cartouches. Certains blockhaus de la BEF en furent équipés, elles étaient posées sur des socles métalliques. Elle a été refroidie par eau à l'aide d'un tuyau.

Des soldats inspectent une vickers (photo : imperial war museum)

Un socle pour une mitrailleuse Vickers.

Les Fusil-Mitrailleurs (armes automatiques portatives)

-le Fusil-Mitrailleur 24/29

Le Fusil-Mitrailleur 24/29 (FM 24/29) était un Fusil-Mitrailleur Français conçu en 1924 puis modifié en 1929. Il avait une cadence de tir de 450 coups/minute et avait un chargeur de 25 cartouches.

utilisation dans les blockhaus : France de 1937 à 1939

Un FM 24/29 sur une porte de type A à la casemate du mont des bruyères.

-le Fusil-Mitrailleur BREN MK1

Le Fusil-Mitrailleur BREN MK1 était un Fusil-Mitrailleur Anglais conçu en 1935. Il avait une cadence de tir de 500 coups/minute et avait un chargeur de 30 cartouches.

Un Bren mk1 servit par des hommes de la BEF (photo : imperial war museum)

utilisation dans les blockhaus : BEF de 1939 à 1940.

Les Fusil Antichars

-le Fusil Antichar Boys

Le Fusil Antichar Boys était un Fusil antichar Anglais conçu en 1937. Il avait une cadence de tir de 10 coups/minute et avait un chargeur de 5 cartouches de 13.9mm.

Un fusil antichars Boys (photo : imperial war museum)

utilisation dans les blockhaus : BEF de 1939 à 1940

Des soldats de la BEF dans un blockhaus Français, au centre un fusil mitrailleur Bren, à droite un fusil antichar Boys. (photo : imperial war museum)

Les soldats utilisent aussi des fusils ENFIELD MK3 dans les pillbox.

Les créneaux de tirs des blockhaus changent en fonction des armes utilisées.

Pour les blockhaus Français :

Les créneaux pour canons et mitrailleuses.

Vue extérieure.

Vue intérieure.

Les créneaux pour mitrailleuses.

Créneau pour mitrailleuse hotchkiss 8mm.

Les créneaux pour fusils-mitrailleurs.

Créneau simple pour Fusil-Mitrailleur.

Créneau blindé pour Fusil-Mitrailleur (auteur : Erwan Merlin)

Pour les pillboxes de la BEF :

Les créneaux pour fusils-mitrailleurs.

Contrairement aux blockhaus français, les pillboxes de la BEF n'ont pas de créneaux standards.

Grand créneau pour FM voir pour un Boys.

Créneau moyen pour FM voir pour un Boys.

Petit créneau pour FM.

Créneau blindé pour FM.

Les créneaux pour canons et mitrailleuses.

Les créneaux pour canons étaient construits avec des rails métalliques sur les extrémités du créneau.

Un créneau pour canon.

6.L’organisation défensive autour de Lys Lez Lannoy

Autour de Lys Lez Lannoy, de gros travaux ont aussi lieu. A Leers, 5 Blockhaus sont construits en 1937 et une tourelle démontable est posée. Puis 4 pillboxes on était construits.

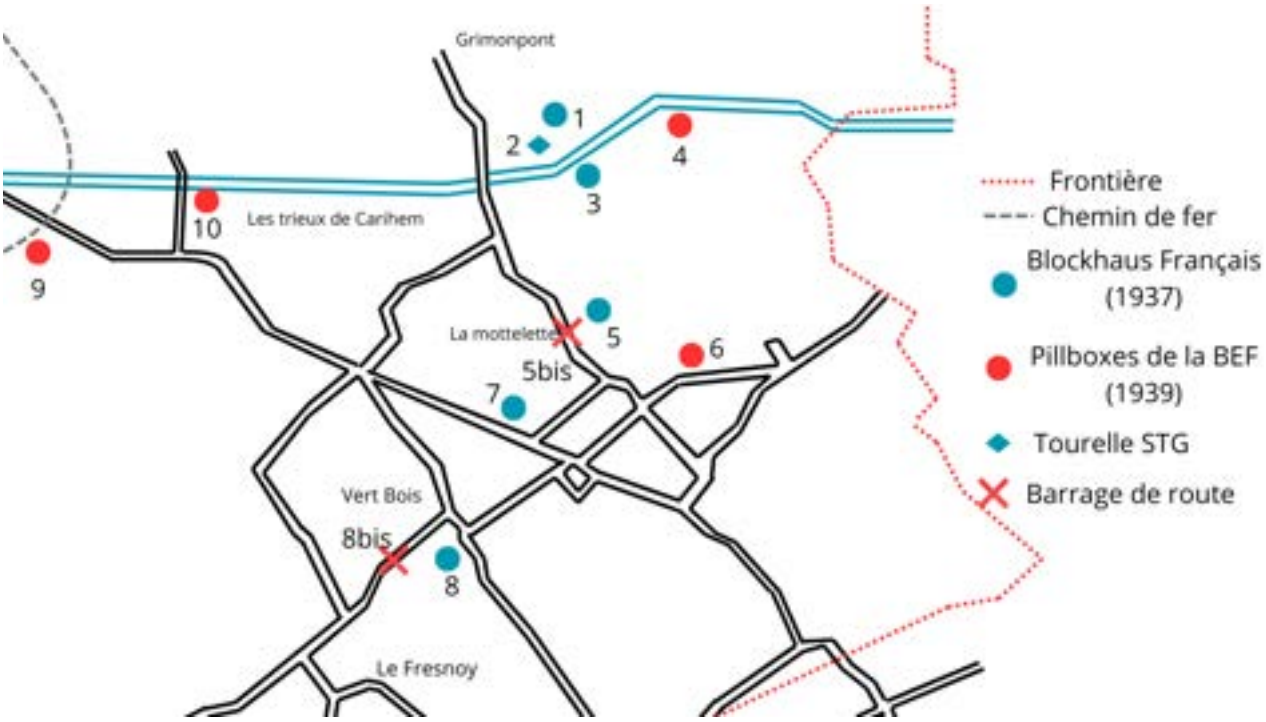

Plan du secteur de Leers en 1940.

Dénomination	Type de construction	Constructeur	Numéro
Le Canal	Bloc type Gsg	16ème RRT	1
Tourelle du canal	Turelle STG	-	2
Le Mur	Bloc type N1f	16ème RRT	3
Couture de l’Avril	Pillbox type U1	BEF	4
La Mottelette	Bloc type Dd	16ème RRT	5
-	Barrage de route	-	5bis
La Mottelette	Pillbox type R	BEF	6
Le Buisson Sud	Bloc type G2	16ème RRT	7
Vert Bois	Bloc type Gsd	16ème RRT	8

-	Barrage de route	-	8bis
Les Trieux de Carihem Ouest	Pillbox type U2g	BEF	9
Les Trieux de Carihem Est	Pillbox type U2g	BEF	10

Le bloc du canal avait une particularité car il était relié par tranché à la tourelle STG du canal.

Le pillbox des trieux de Carihem Est.

À Wattrelos, de nombreux blockhaus sont construits notamment à Beaulieu.

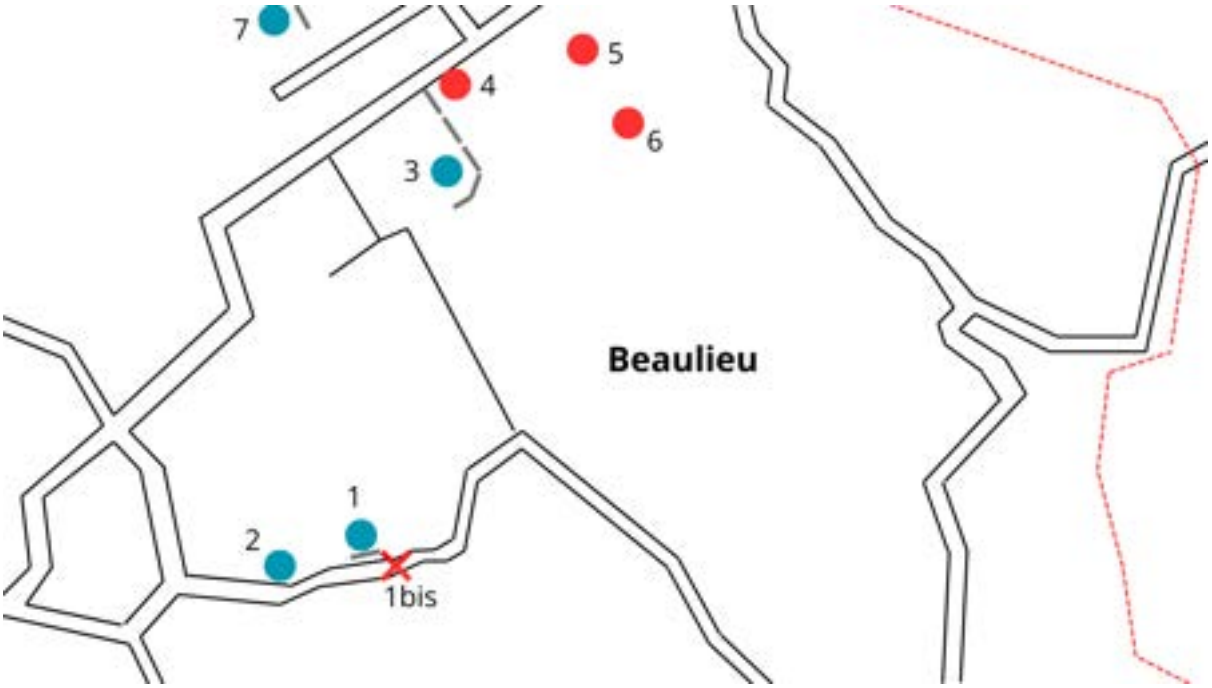

Plan du secteur de Beaulieu en 1940.

Dénomination	Type de construction	Constructeur	Numéro
Grimonpont Nord	Bloc type Dsg	16ème RRT	1
-	Barrage de route	-	1bis
Grimonpont Sud	Bloc type N1f	16ème RRT	2
Beaulieu Sud	Bloc type Dsd	16ème RRT	3
Gauquier Ouest	Pillbox type W3g	BEF	4
Gauquier Nord	Pillbox type R	BEF	5
Gauquier Est	Pillbox type R2	BEF	6
Beaulieu Nord	Bloc type Da	16ème RRT	7

Le bloc de Beaulieu Sud.

Schéma de l'organisation du réseau anti-char

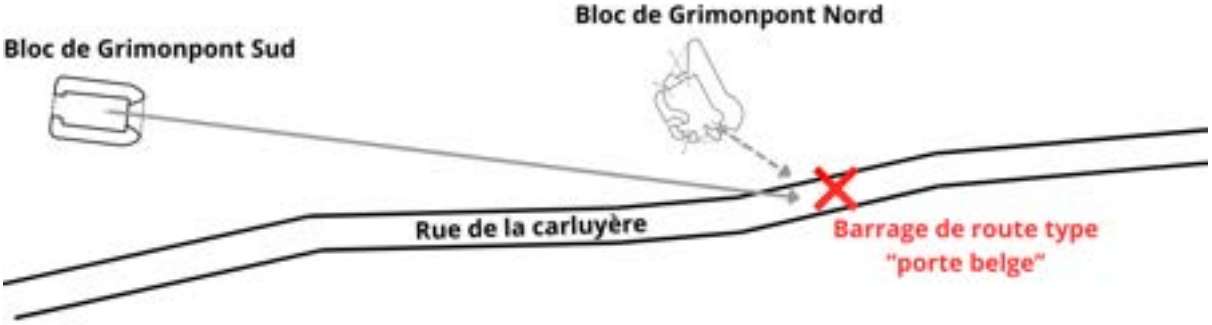

Schéma de l'organisation défensive anti-véhicules rue de la carluyère.

Le bloc de Grimonpon Nord.

Comme expliqué dans le premier chapitre, le 406ème RAA se positionne à Beaulieu.

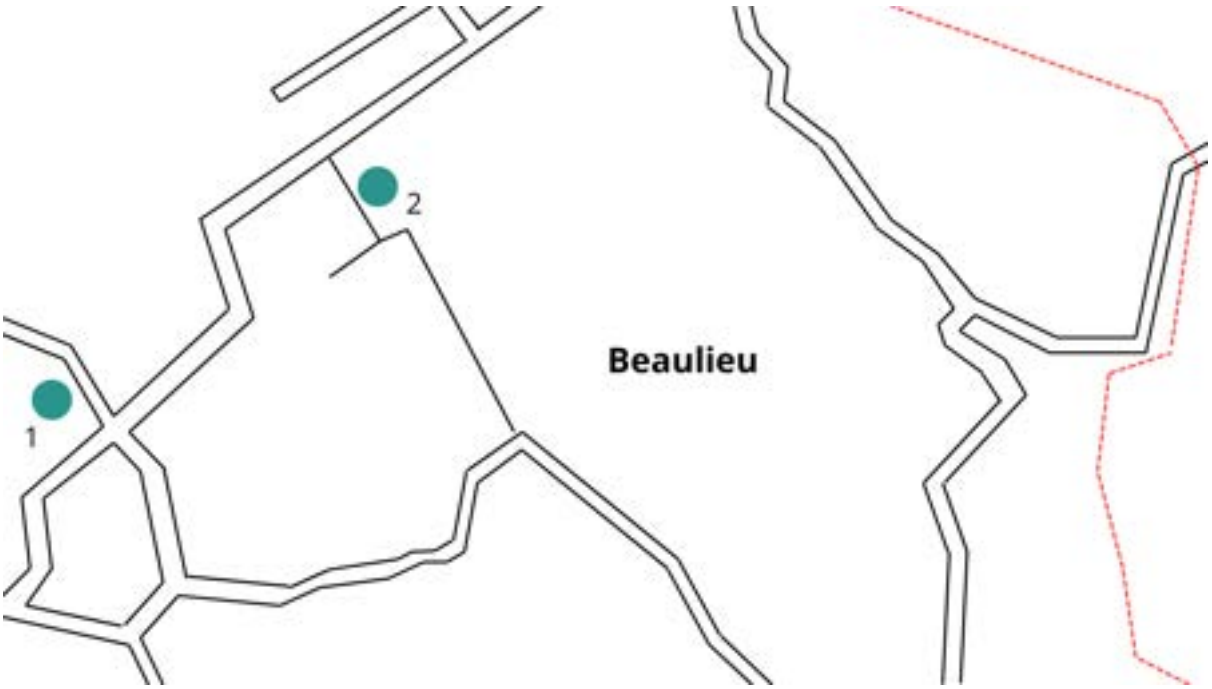

Une première batterie de mitrailleuses de 13.2mm jumelées était positionnée (1) et une seconde pour 4 canons de 75mm antiaériens placées dans des cuves bétonnées (2).

Plus au sud, à Hem, la BEF a réquisitionné le château Pollet (plus communément appelé “le château de la Marquise”) et y installe un poste de commandement, celui-ci est du IIème corps du BEF. Le château a pour nom de code “Green Shutters” (Volets Verts) et les fermes jumelles sont nommées “Twin Farms” (Fermes Jumelles). Autour du PC, de nombreux pillbox ont été commencées mais les trois quarts n’ont pas pu être finalisés.

Du côté de la ligne principale, des travaux de défenses ont aussi été faits par les Britanniques.

Cette ligne est constituée sur la commune de Hem de 13 blockhaus (6 Français et 7 Britanniques) et 3 non finalisés. Notons aussi un emplacement pour une tourelle STG.

Des tranchées sont creusées ainsi qu'un fossé antichars. Le ruisseau de la Marque à été utilisé comme obstacle antichars.

Des soldats creusent des tranchées à Hem.
(photo : Imperial War Museum)

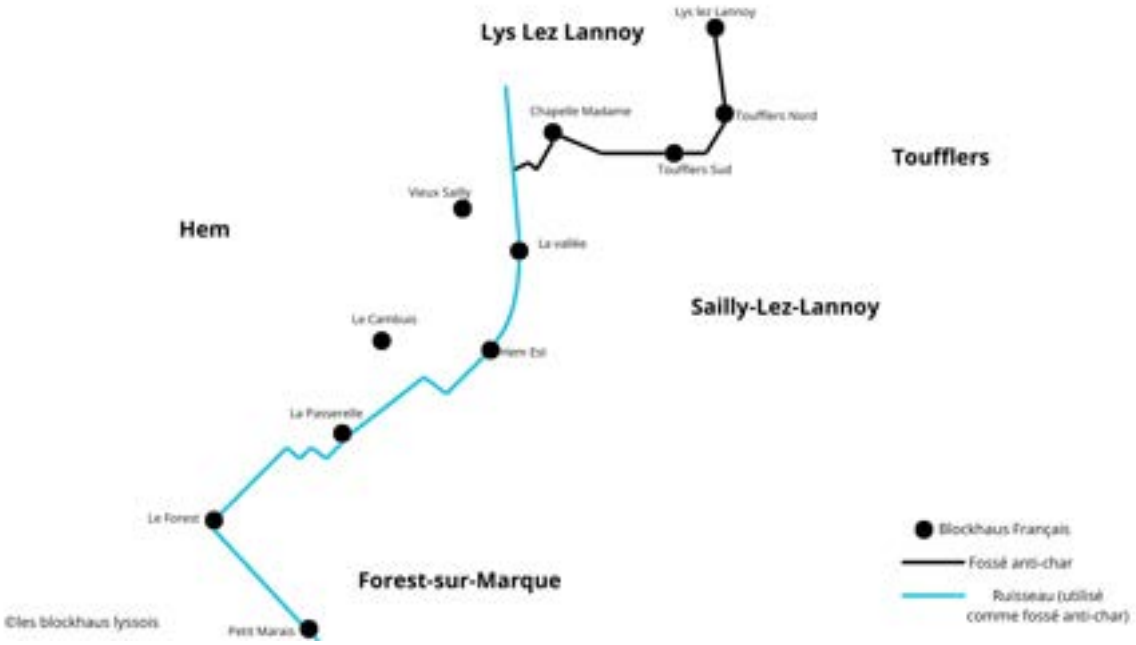

Carte des fossés antichars de Lys Lez Lannoy à Forest-sur-Marque.

Le bloc de la chapelle madame.

À proximité : un rail antichar.

7. Le Secteur Fortifié de Lille en général

Le SFL n'a été créé qu'en 1937 mais les ingénieurs n'avaient pas décidé tout de suite de faire passer la ligne par la frontière mais plutôt du côté de la bassée (tracé de 1932), mais cette idée ne verra jamais le jour. En 1937, après la déclaration de neutralité de la belgique, il est décidé de faire passer la ligne le long de la frontière pour rassurer les industriels de la région pour ne pas revivre le sort de la grande guerre. Cela sera une mauvaise idée car le terrain est plat, il n'y a pas de zones inondables et c'est une zone très urbanisée, cela causera beaucoup de trous dans le dispositif comme à Tourcoing. Les britannique ont appelé cette ligne la "Gort Line" (Ligne Gort) car Lord Gort était le chef des armées britanniques en France.

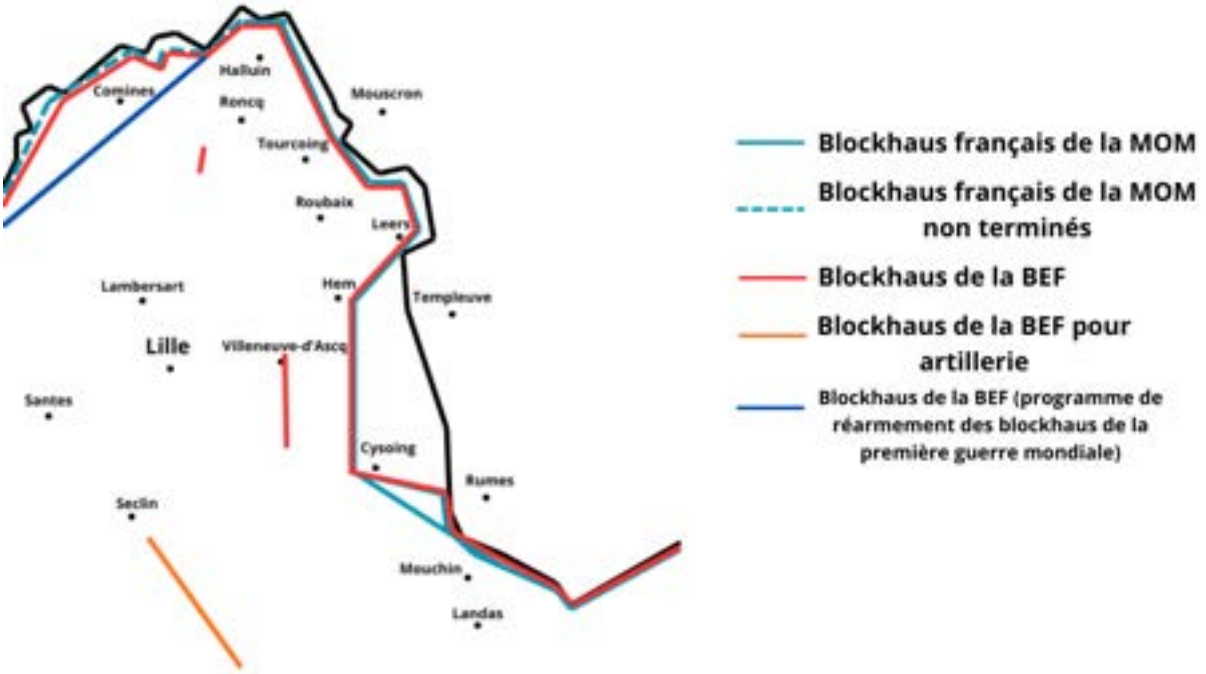

Carte du Secteur Fortifié de Lille.

Le secteur s'étendait de manière significative, couvrant une zone allant d'Halluin au nord-ouest à Lecelles au sud-est (une ligne était en projet en 1940 de Halluin à Armentières mais seuls quelques blocs ont pu être finalisés). Il se positionne entre le Secteur Fortifié des Flandres à sa limite nord-ouest et le Secteur Fortifié de l'Escaut vers le sud-est.

Conçu comme une partie intégrante de la ligne Maginot, le SFL visait à renforcer la défense de la France contre d'éventuelles agressions. Au fil du temps, il a évolué de 'Secteur Défensif' à 'Secteur Fortifié', témoignant d'une adaptation aux doctrines militaires et aux menaces perçues.

Des blockhaus Allemands de la première guerre mondiale ont aussi été réutilisés par les troupes de la BEF vers Halluin et une seconde ligne était prévue vers Haubourdin.

En tout, plus de 700 constructions bétonnés (blockhaus) furent en projet, en cours de construction ou construits en mai 1940.

Lors de l'arrivée allemande en 1940, certains blockhaus n'avaient pas eu le temps d'être finalisés.

Un blockhaus de type R qui n'a pas eu le temps d'être terminé.

8. La drôle de Guerre

Entre le 3 septembre 1939 et le 10 mai 1940, les soldats ne bougent pas de leurs positions et améliorent leurs positions de jour en jour. C'est le début de la Drôle de Guerre. Cette expression vient du terme Anglais "phoney war" (fausse guerre) et par une erreur de compréhension en français qui devient "funny war" (drôle de guerre).

Pendant ce temps, les soldats construisent des pillboxes, creusent des tranchées, aident les agriculteurs aux champs, jouent au football,... Mais malgré ça, les soldats s'ennuient dans leurs positions. Pour remédier à cela, l'État français offrait des produits détaxés comme par exemple des cigarettes.

A partir de novembre 1939, les choses se compliquent encore plus car les conditions météorologiques se dégradent. Les soldats sont obligés d'acheter des bottes pour remédier au problème de la boue. De plus, les routes se dégradent aussi car les pavés glissent dans les fossés.

En décembre 1939 le roi George VI inspecte les troupes de la BEF.

Le roi George VI sur un blockhaus à Bachy (photo : imperial war museum)

La neige s’invite aussi, l’ennemi n’attaquera pas dans la neige ! Les entraînements continuent dans la neige.

Le 25 Décembre, les soldats fêtent noël dans les fermes. Des cartes sont offertes aux soldats, certains en feront de véritables œuvres d'art !

Les soldats fêtent Noël dans une ferme à Mouchin (photo : Imperial War Museum).

9. Les combats

LE SOIR

FILS SPÉCIAUX AVEC PARIS ET LONDRES

LE NOUVEAU CRIME HITLÉRIEN

L'Allemagne attaque la Belgique, la Hollande et le Luxembourg

La brutale agression n'a été précédée d'aucun ultimatum, d'aucune démarche diplomatique

La Belgique fait appel à la France et à l'Angleterre

Les troupes franco-britanniques sont en marche

Vive le Roi! Vive la Belgique!

Le crime allemand

Déclaration de M. Spaak à l'Ambassadeur d'Allemagne

L'AGRESSION

Des aéroplanes ont été lancés

Attentat aux parachutistes et aux saboteurs

Les attaques aériennes

Signaux d'alerte

Le Gouvernement décrète la mobilisation générale et l'état de siège

Les combats vus par les soldats

Le 10 Mai 1940, l'allemagne envahit les pays du bénélux comme prévu par l'état major. Les troupes franco-britanniques franchissent la frontière pour prêter main-forte aux Belges.

Des soldats britanniques franchissent la frontière belge à herseaux. Photo : Imperial War Museum.

A leur arrivée en belgique, les soldats font face aux panzers allemands et aux bombardiers. Les soldats sont gênés par l'exode des civils, fuyant les bombes.

Le 13 Mai 1940, un événement inattendu se produit ! Les Allemands sont rentrés en France par les Ardennes ! Une région très peu fortifiée car selon les généraux français "Les chars allemands ne pourront pas passer par la forêt des Ardennes" pourtant, il y parviennent !

Il est donc décidé de se replier pour contre-attaquer. Malgré des résistances héroïques, les chars allemands arrivent à passer et foncent vers le nord.

Les positions en Belgique sont abandonnées et de nombreuses routes sont coupées.

Suite à la percée dans les Ardennes, les allemands remontent vers le nord, puis coupent les armées franco-britanniques dans le nord. L'armée française et l'armée britannique se retrouvent encerclés dans le nord, maintenant, il ne s'agit plus de repousser mais d'évacuer ! Toutes actions entreprises contre l'ennemi sont des actions de retardement pour évacuer à Dunkerque.

Le 24 Mai 1940, des combats éclatent dans la ville de Wattrelos, les combats se font dans
la plaine de Beaulieu et au quartier de la Martinoire avec des soldats du Suffolk Regiment, Royal Berkshire et du East Yorkshire. Quelques blockhaus servent mais, contraint de se replier le 27 Mai, les soldats Anglais abandonnent leurs blockhaus. 31 soldats britanniques perdirent la vie dans les combats.

Wattrelos était un axe stratégique car le pont du sartel était le seul à ne pas avoir été détruit ce qui à permis aux allemands de passer plus facilement.

Un pillbox dans la plaine de beaulieu à Wattrelos ©les blockhaus lyssois

À Leers, les Anglais minent le carrefour de la rue Victor Hugo et la rue de Wattrelos pour ralentir l'avancée allemande. L'explosion fera exploser la moitié de la rue Victor Hugo. Dans la précipitation, les Anglais, ne pouvant faire passer leurs engins, firent sauter une partie des bâtiments de la ferme DROULEZ Félix. Ceux-ci ne furent jamais reconstruits en raison du projet d'urbanisation de la rue de Lys. Le carrefour de la rue de lys fut aussi miné.

À Lys Lez Lannoy, il n’y a pas eu de gros combats mais des tirs furent quand même échangés. Les britanniques ont abandonné les blockhaus et ont évacué.

À Hem, les combats se déroulent au Civron, rue de Sailly, rue du Calvaire et rue Jules Guesde. Les Britanniques font sauter les ponts. Une quinzaine de militaires allemands ont trouvé la mort derrière la briqueterie de Hem.

Dans le secteur fortifié de Lille en général, les combats se font autour de cysoing.

Le 28 Mai 1940, Lys Lez Lannoy est sous couleurs allemandes. Les jours sombres ne venaient seulement de commencer…

Les combats vus par les civils

Le **19 mai 1940**, la situation devient critique.
Dans les villages proches de la frontière, les habitants fuient précipitamment devant l'avancée allemande. Charrettes, bicyclettes et voitures surchargées envahissent les routes tandis que les bombardements obligent les civils à se jeter dans les fossés pour se protéger.

"Je me souviens que le 19 Mai 1940, mon papa est rentré de la messe en criant "on doit évacuer !".
Mettez vous à la place de ma mère, partir avec 8 enfants. Pas de voiture. Papa s'est débrouillé pour une calèche conduite avec des chevaux. Quel branle-bas de combat à la maison !
Maman a cuit dur tous les œufs qu'ils restaient, je me rappelle, nous les avons enveloppés dans une valise.
On a fait chacun notre bagage. On a pris les restes du repas : un bon rôti avec de la sauce. A 15H, nous voilà partis, avec la famille famille Dupont [...]
Arrivés à la descente du beau jardin, les chevaux se sont emballés, je me souviens encore que les garçons criaient : "Oh hisse !", pour eux, c'était la fête ! On a eu de la chance que des anglais étaient au bord du lac, ils ont su les arrêtés.
Nous voila partis direction Hazebrouck, dans un orphelinat, on pouvait dormir la mais on a vu M.Henry Deroubaix, capitaine de l'armée, qui nous conseille de ne pas rester là car la gare, qui était tout près, allait être bombardée. On est donc repartis dans une ferme chez les Degrave, qui ont bien voulu nous accueillir.
On logeait dans une cave à pommes de terres, on a répandu de la paille avec des grandes toiles de jute et je peux vous dire qu'on a bien dormi !
Le lendemain, nous apprenions que l'orphelinat était complètement rasé par les bombes.
Le 22 mai, j'ai fêté mon anniversaire. Je ne me rappelle plus comment nous les avons souhaité mais je sais que toute la famille était réunie.
Dans la ferme, il y avait des Anglais, qui avaient fait leur camp. Puis les Allemands sont arrivés, on s'était enfermés dans la cave. Plusieurs Anglais ont été tués.
Les Allemands sont venus dans la cave, baïonnette au poing, on criait "réfugiés,réfugiés", on a vraiment eu peur.
Au bout de quelques jours, des espions allemands sont venus dire à nos parents que la ferme, dans laquelle on était, allait être bombardée et que pour les jeunes enfants c'était dangereux.

Mais où aller ? En effet, le soir, je ne saurai pas dire combien de bombes sont tombées tout autour de la ferme. Là encore, on s'était mis à l'abri dans la cave.
Je n'ai jamais eu aussi peur de ma vie alors que les 2 petits Maurice et Bernard dormaient dans leur landau sous le hangar. Je me souviens que maman n'osait pas aller les voir. Mais surprise, ils dormaient alors qu'un éclat de bombe avait traversé la capuche de la voiture, c'était un miracle !
Avec les grands-parents, on n'arrêtait pas de prier Notre Dame de Lourdes. Le lendemain, nous sommes partis chez une dame qui nous a donné sa maison en attendant qu'on puisse rentrer à Toufflers.
Je ne sais plus combien de temps nous sommes restés. Les hommes sont retournés à vélo pour voir leurs jardins et quand on a pu rentrer, ils se sont débrouillés pour venir nous chercher.
Je sais qu'avec les garçons, on était dans la camionnette de Fernand Duquesnoy. On chantait tout le long de la route.
Quel bonheur de revoir sa maison !
À Toufflers ? Il ne s'était finalement rien passé. On a retrouvé le drapeau français dans les toilettes et sur la table, la valise avec les œufs durs qu'on avait oubliés !”

Témoignage d'Agnès Dillies,
habitante à Toufflers lors de l’évacuation.

Les civils évacuent devant un BREN carrier. Photo : Imperial War Museum.

10. L’après guerre jusqu'à aujourd’hui

Après la Guerre, ces blockhaus sont tombés peu à peu dans l’oublis, les blockhaus français se sont vu retirer les parties métalliques pour en garder le métal. Certains ont été récupérés pour en faire des étables, des abris de jardins ou même des habitations et les tranchées ont été rebouchées.

Lors de l’urbanisation, beaucoup de blockhaus furent détruits pour laisser place à des immeubles ou des maisons. De même dans les champs car ils occupaient une place non cultivable trop importante.

Aujourd’hui, il ne reste plus que les blockhaus, mastodontes de béton au milieu des champs. Ce qui nous laisse réfléchir sur le sacrifice de ces soldats morts pour la liberté.

“Never forget”

“Ne jamais oublier”

10b. La ligne aujourd'hui

Le bloc de la vallée.

Le bloc du cambuis.

Un pillbox au parc du lion à Wattrelos.

La moitié des blockhaus construits par la BEF ont été détruits. À Lys Lez Lannoy, sur les 10 blockhaus construits, 7 existent toujours. Les 3 démolis ont été victimes des projets d'urbanisation. Le bloc de Lys Lez Lannoy fut détruit en 2005 pour construire le quartier du béguinage et les pillboxes du bon poste Ouest et Est ont été rasées pour construire l’école du petit prince.

Remerciements à

- Erwan Merlin pour les photos et l’écriture.

- Gael Muller pour la publication du livre sur internet.

- Aux propriétaires des blockhaus pour avoir permis de photographier leurs blockhaus.

Table des matières

- Abréviations utilisées : Pages 4-5

- Contexte général : Page 6

- L'entre deux guerres : Page 7

- La mobilisation des troupes : Pages 8-9

- Les blockhaus : Pages 10-39

- L'armement de la Ligne : Pages 40-50

- **L'organisation défensive autour de Lys Lez Lannoy :** Pages 51-58

- **Le Secteur Fortifié de Lille en général** : Pages 59-60

- **La drôle de Guerre** : Pages 61-62

- **Les combats** : Pages 63-68

- **L'après guerre jusqu'à aujourd'hui** : Page 69

- **La ligne aujourd'hui** : Pages 70-71